道路の"かたち"で街がわかる

静岡県3都市の道路ネットワーク比較

焼津市 ・ 静岡市 ・ 浜松市

グラフ理論による道路ネットワーク構造の定量比較

2026年3月

道の形は街ごとに違う？

同じ静岡県内でも、歴史や地形が異なれば道路の形も違うはず。
3つの街の道路ネットワークを数値で比べてみました。

焼津市

漁港の街

駿河湾に面した漁港都市。
旧来の漁村集落に由来する
細い路地が残る。

静岡市

城下町

駿府城の城下町を起源とする
県庁所在地。格子状の
市街地と広大な山間部。

浜松市

工業都市

政令指定都市。近代的な
格子状街路を基盤とする
遠州灘沿いの工業都市。

3つの物差しで道路を測る

回遊性

ぐるぐる歩ける？

道路がループを
どれだけ形成しているか。
多いほど迷い歩きを
楽しめる。

アクセス性

どこでも行ける？

交差点の密度や
ネットワーク上の到達しや
すさ。
高いほど移動の
選択肢が多い。

迂回性

遠回りする？

最短経路が直線距離の
何倍になるか。
低いほど効率的に
移動できる。

※ 劉（2016）の3観点に基づく道路ネットワーク評価フレームワーク

小さな焼津市が一番"つながっている"

市全域の道路ネットワーク比較

コンパクトな焼津市が回遊性・アクセス性で

3市中トップ。

広大な山間部を含む静岡市・浜松市は
市全域でみると数値が低くなる。

注目ポイント

焼津市の交差点密度は静岡市の約5倍
静岡市は迂回性が最も高い（山間部の影響）

市域面積: 焼津70km² vs 静岡1,412km² vs 浜松1,558km²

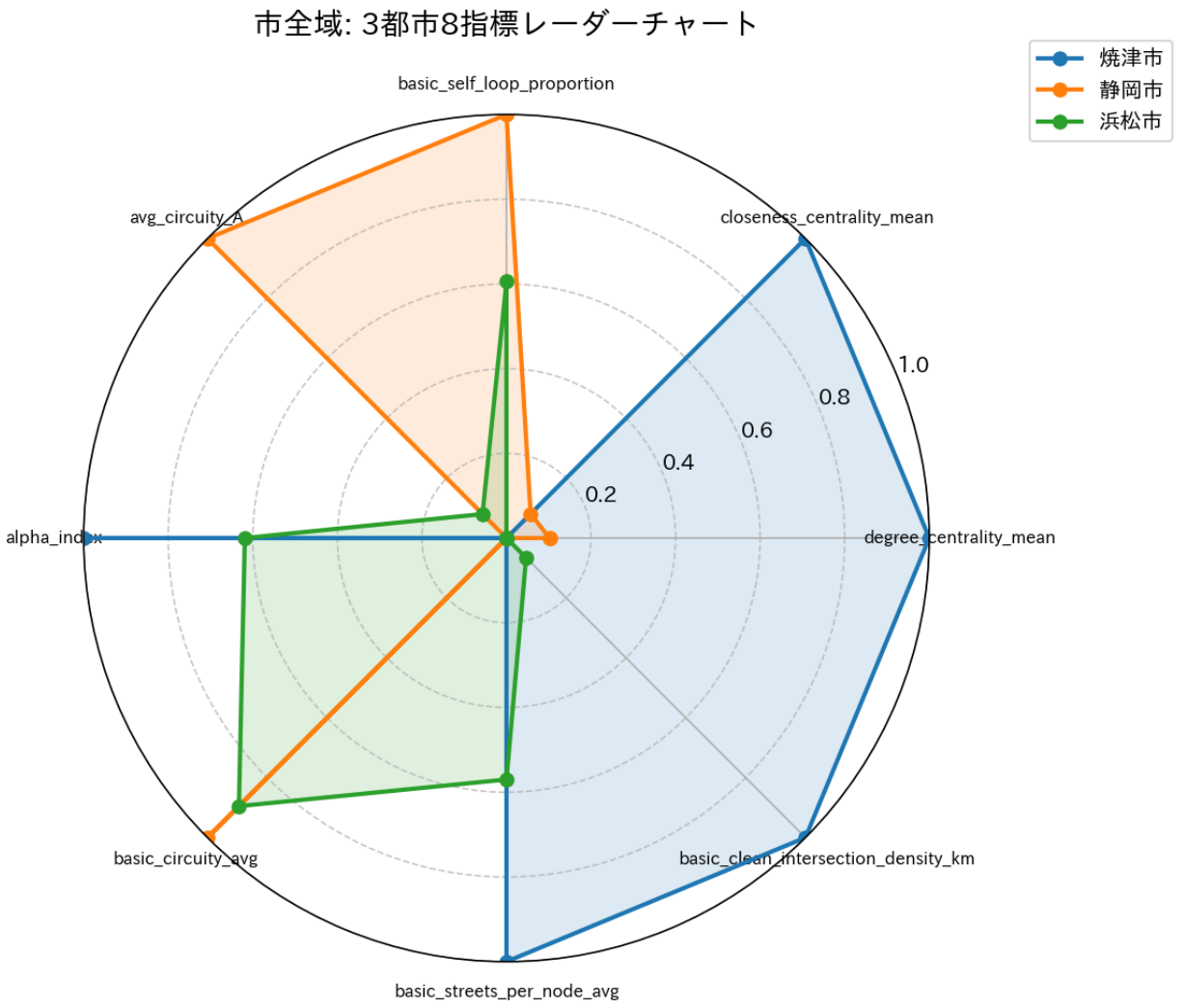

海沿いの方が道が充実していた

沿岸部 vs 内陸部の比較（仮説を覆す結果）

当初の仮説:

「沿岸部は回遊性が低く、迂回性が高い」

実際の結果:

3市すべてで沿岸部の回遊性が内陸部より高い！

なぜ？

沿岸平野部に市街地が集中 → 格子状の道路網が発達

内陸の山間部は谷筋に沿った一本道（樹枝状）が多い

浜松市では沿岸部の交差点密度が内陸部の4.6倍

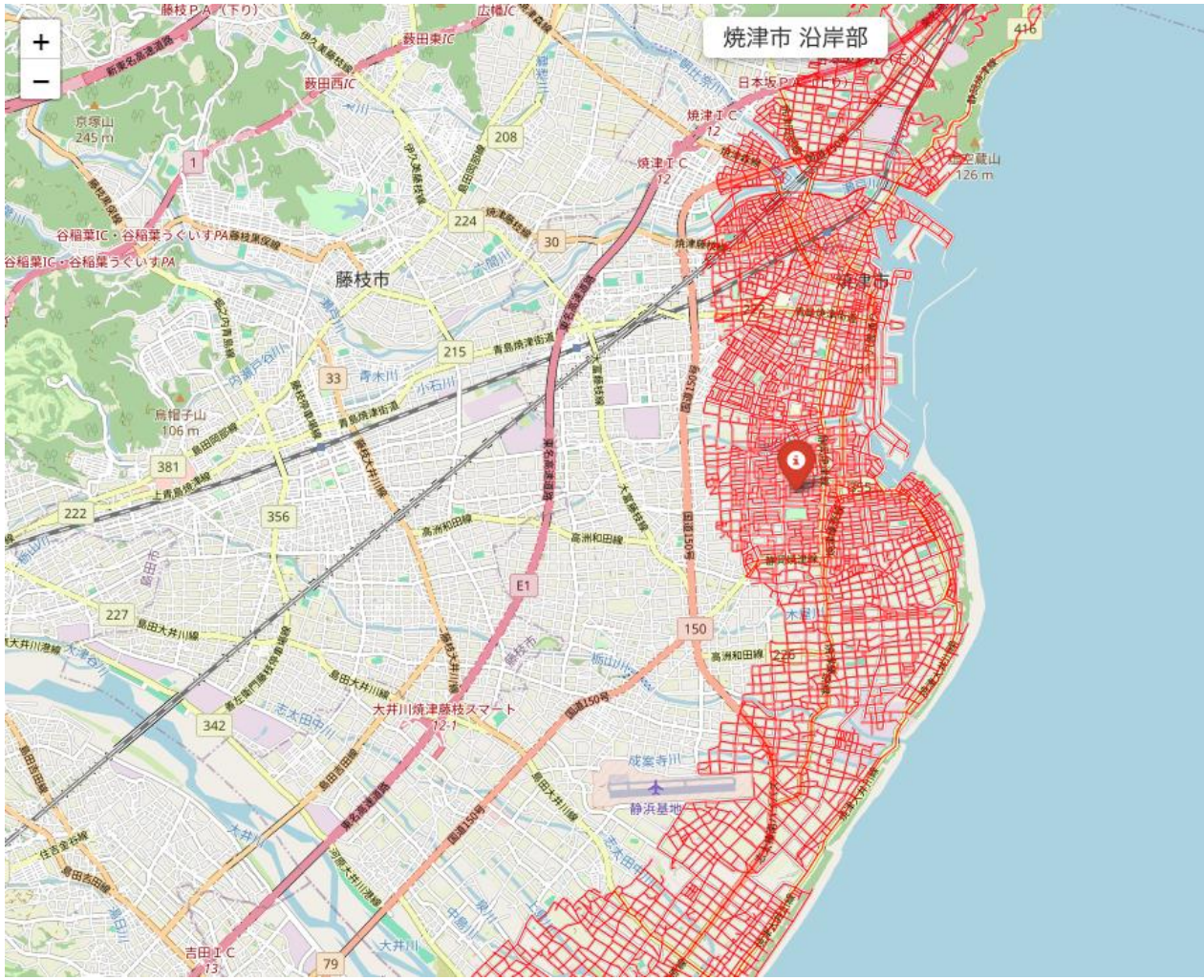

3市の沿岸部ネットワーク

海岸線から2km以内の道路ネットワーク地図

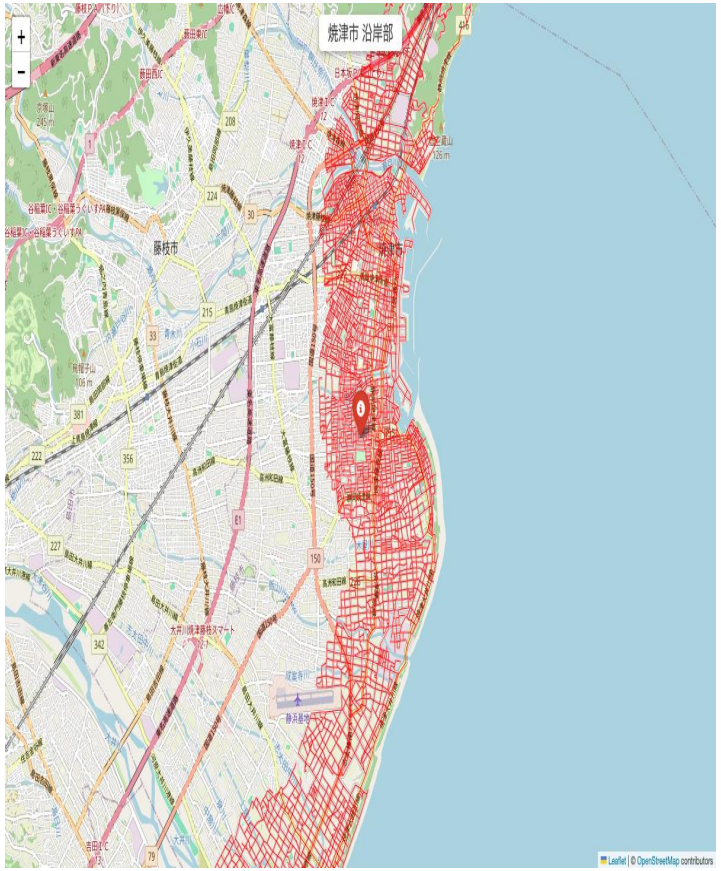

焼津市

回遊性 最高 (0.286)

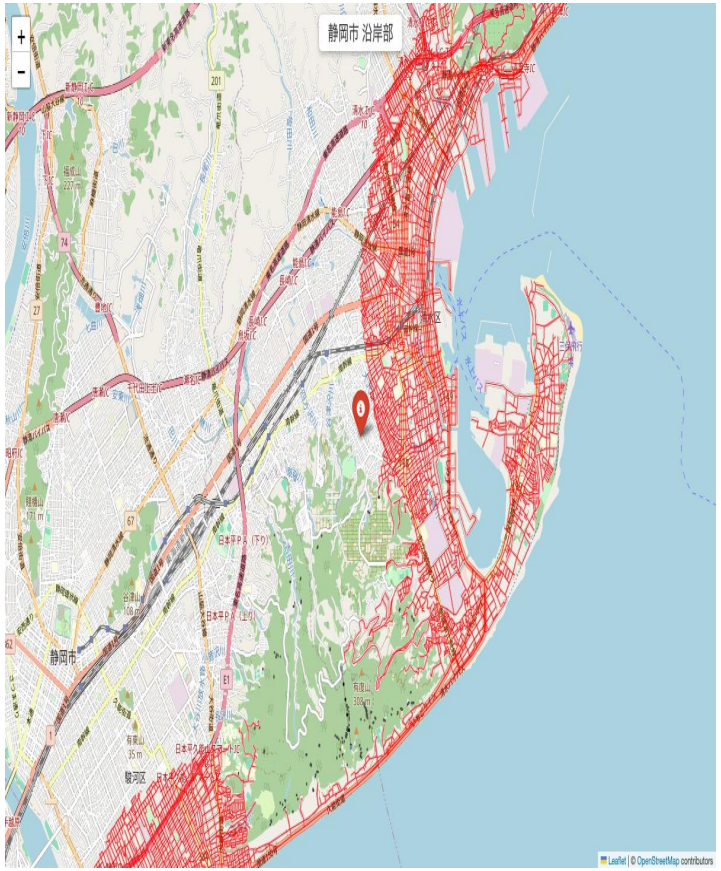

静岡市

迂回性 最高 (1.306)

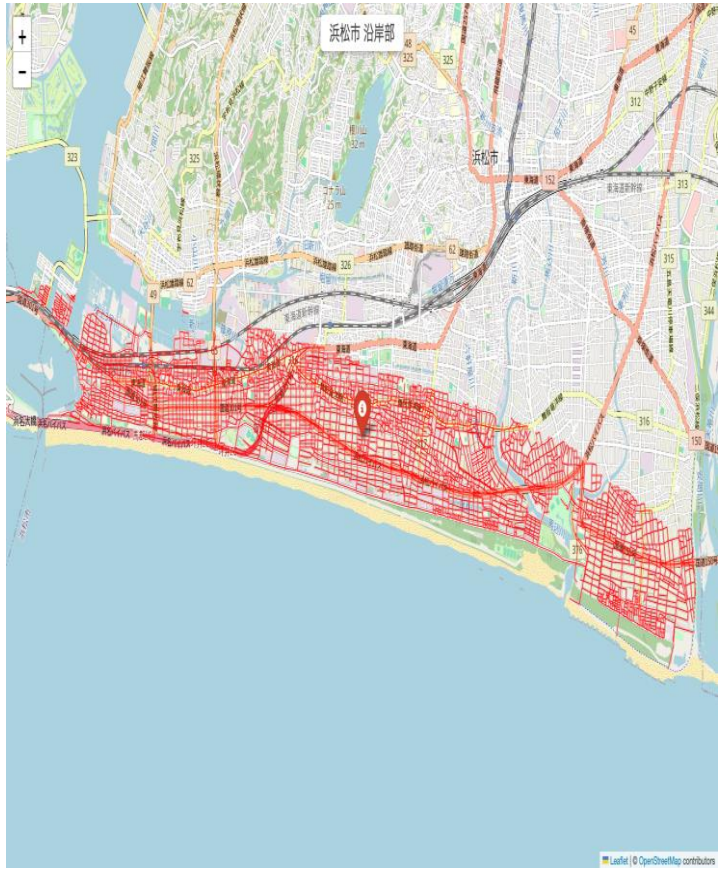

浜松市

迂回性 最低 (1.118)

静岡市の海沿いは"遠回り"が最も多い

防災上の懸念

静岡市沿岸部の迂回率: 1.306

最短経路でも直線距離の約1.3倍を迂回する。

津波避難時に距離が延びるリスク。

原因: 日本平・有度山の丘陵地

清水区と駿河区の間に位置する丘陵地が道路ネットワークを

南北に分断している。

3市の沿岸部 迂回率の比較:

浜松市: 1.118（最も低い = 直線的）

焼津市: 1.199

静岡市: 1.306（最も高い = 遠回り）

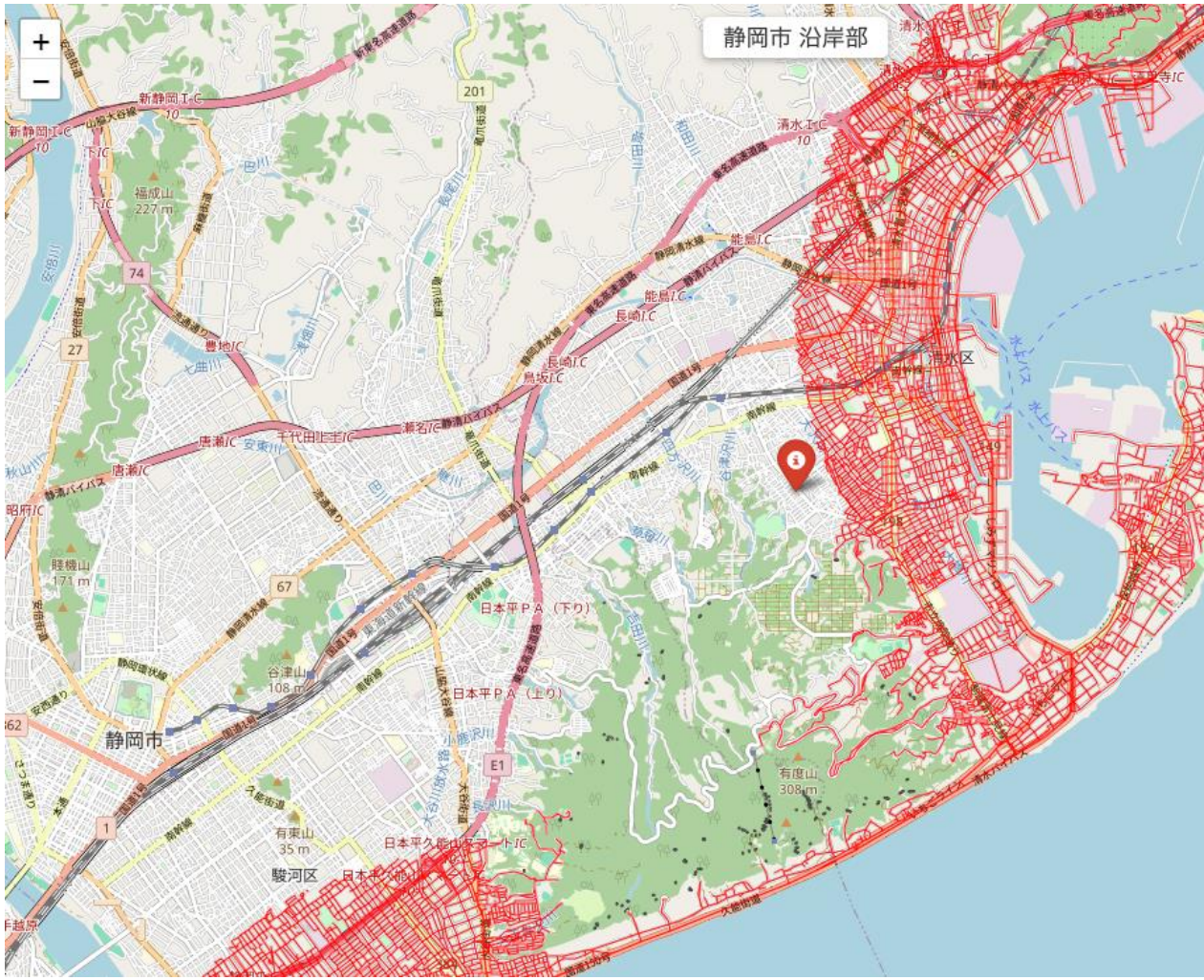

焼津駅が一番"歩き回りやすい"

駅周辺800mの歩行者ネットワーク比較

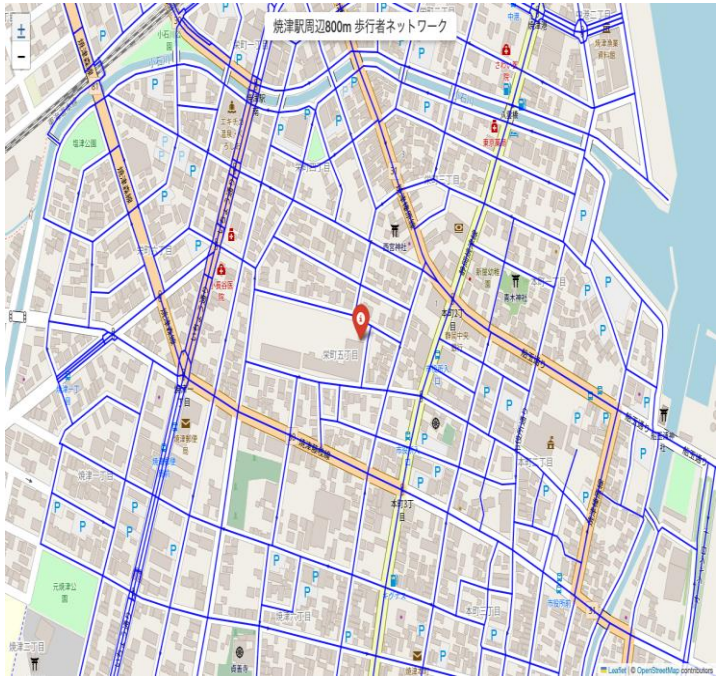

焼津駅
alpha = 0.330

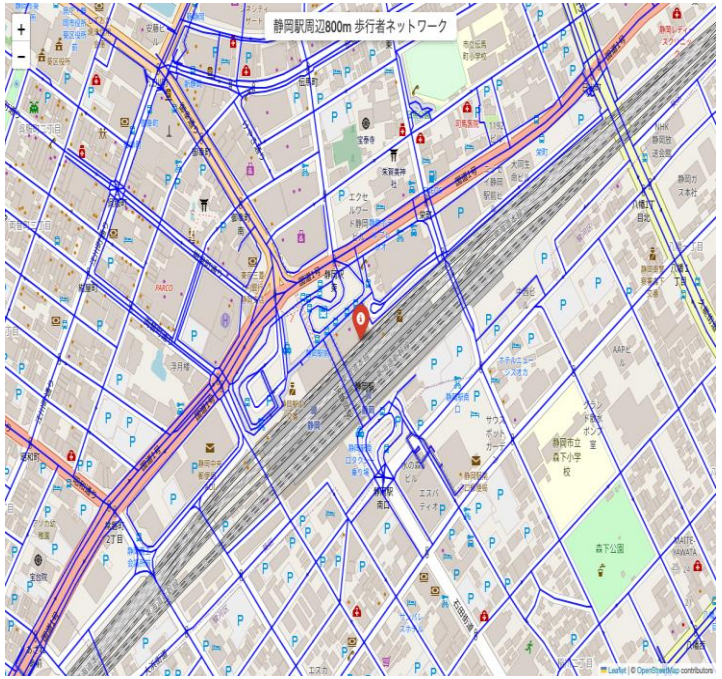

静岡駅
alpha = 0.308

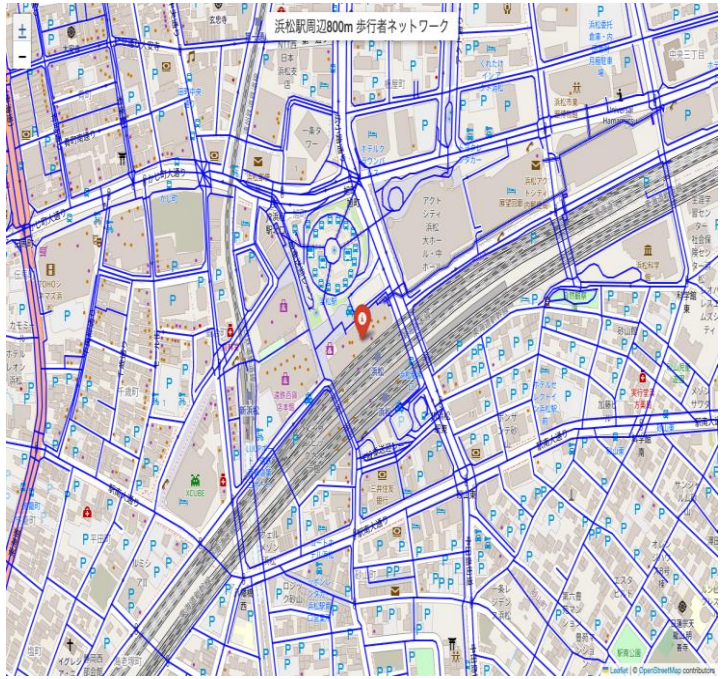

浜松駅
alpha = 0.247

意外にも地方都市の焼津駅が最高の回遊性。

旧漁村集落の細かい路地が、歩行者にとって多様なルート選択を可能にしている。

浜松駅は交差点密度こそ最高だが、大きな街区が回遊性を下げている。

古い路地が街の回遊性を高める

細街路効果: walk と drive の差

歩行者用の細い道（路地・小路）を加えると
回遊性はどう変わる？

walk（歩行者）と drive（自動車）のネットワークの差で
"細街路効果"を測定。

焼津駅
alpha差分: +0.013

路地が循環路を形成
→ 回遊性UP

静岡駅
alpha差分: -0.005

ほぼ中立
城下町の横丁が
一部寄与

浜松駅
alpha差分: -0.029

行き止まりの路地が多い
→ 回遊性DOWN

alpha差分 = walk時のalpha_index − drive時のalpha_index。プラスは細街路が循環路を形成していることを示す。

3都市の個性

ネットワーク特性プロファイル

焼津市 — コンパクト高回遊型

小さな市域に道が密集。路地が
回遊性を高め、迂回も少ない。

静岡市 — 広域高迂回型

城下町の中心部は歩きやすいが、
広大な山間部が市全域の数値を下げる。
沿岸部の遠回りに防災上の課題。

浜松市 — 近代格子・大街区型

交差点は密だが大きな街区で
回遊性は低い。
沿岸部は直線的で避難に有利。

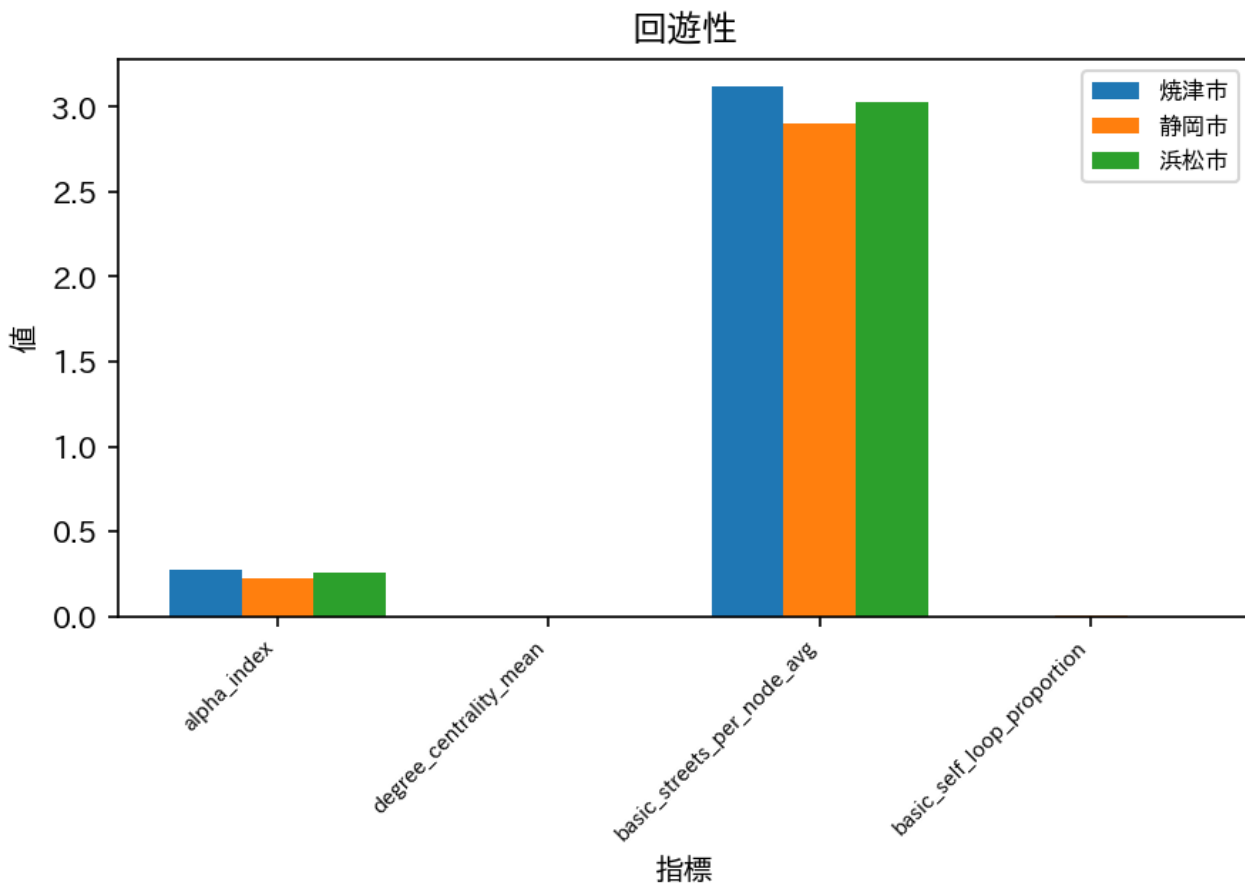

まとめ — 4つの発見

1. **沿岸部は意外と"つながっている"**
   3市すべてで沿岸部の回遊性が内陸部より高い。沿岸平野部に市街地が集中しているため。

2. **静岡市の海沿いは"遠回り"が多い**
   日本平・有度山の丘陵地が道路を分断。迂回率1.306は3市の沿岸部で最も高く、津波避難時の懸念。

3. **焼津駅は"歩き回りやすさ"No.1**
   旧漁村の路地が循環路を形成し、回遊性指標は3駅中トップ。地方都市の隠れた資産。

4. **古い路地こそ街の宝**
   焼津は細街路が回遊性を高め、浜松は行き止まりが増える。道路の"質"は都市の歴史で決まる。

ご清聴ありがとうございました

道路の"かたち"で街がわかる

静岡県3都市の道路ネットワーク比較

データ: OpenStreetMap / 分析: OSMnx + NetworkX